日本南岸海域（中央ブロック）を特徴づける海洋構造

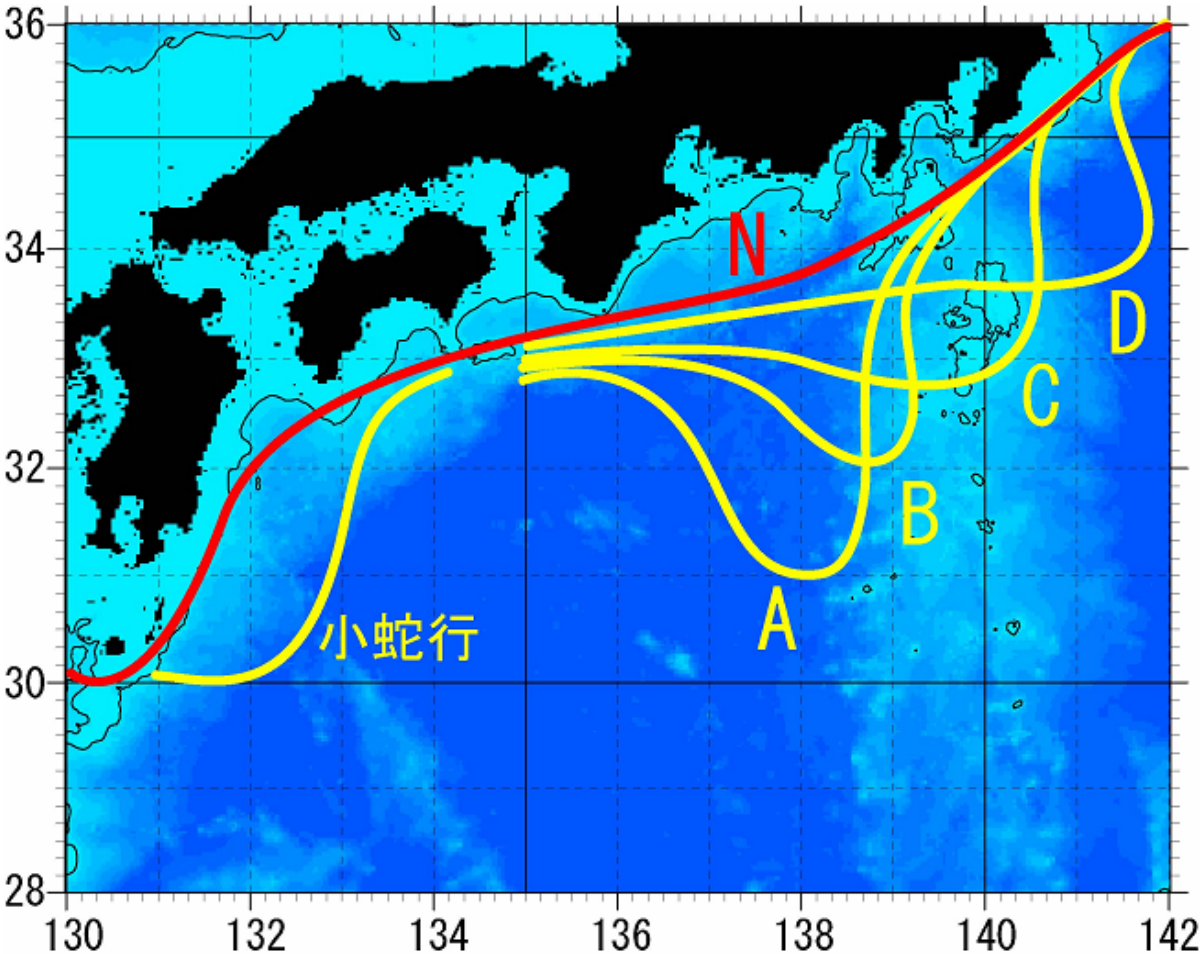

日本南岸海域（中央ブロック）には本州南岸に沿って黒潮が流れています。黒潮の流路・流量は変動が大きく，岸近くをまっすぐ流れる場合もあれば，はるか南の方に下がって流れることもあります。岸近くを流れるときに沿岸に黒潮の暖かい水が流れ込み，高温になったり異常潮位を起こす一方，シラスなどを沿岸に運んでくれることもあります。このように，この海域は漁模様も黒潮の動向に左右されることが多く，黒潮がどのように流れているかが大きな関心事となっています。

黒潮の流型

紀伊半島沖から房総半島沖にかけての黒潮の流路は大きく分けて5種類に分類されます。この間をほぼ直進して流れるN型。最も南まで下がり伊豆諸島海域の西を北上するA型(大蛇行)。A型より小さい蛇行のB型。伊豆諸島海域をまたいで蛇行するC型。伊豆諸島海域の東に蛇行があるD型があります。

黒潮小蛇行

九州南東沖で黒潮が離岸することがあります。このふくらみが東に移動することが認められます。これが**黒潮小蛇行**の形成とその東進現象です。

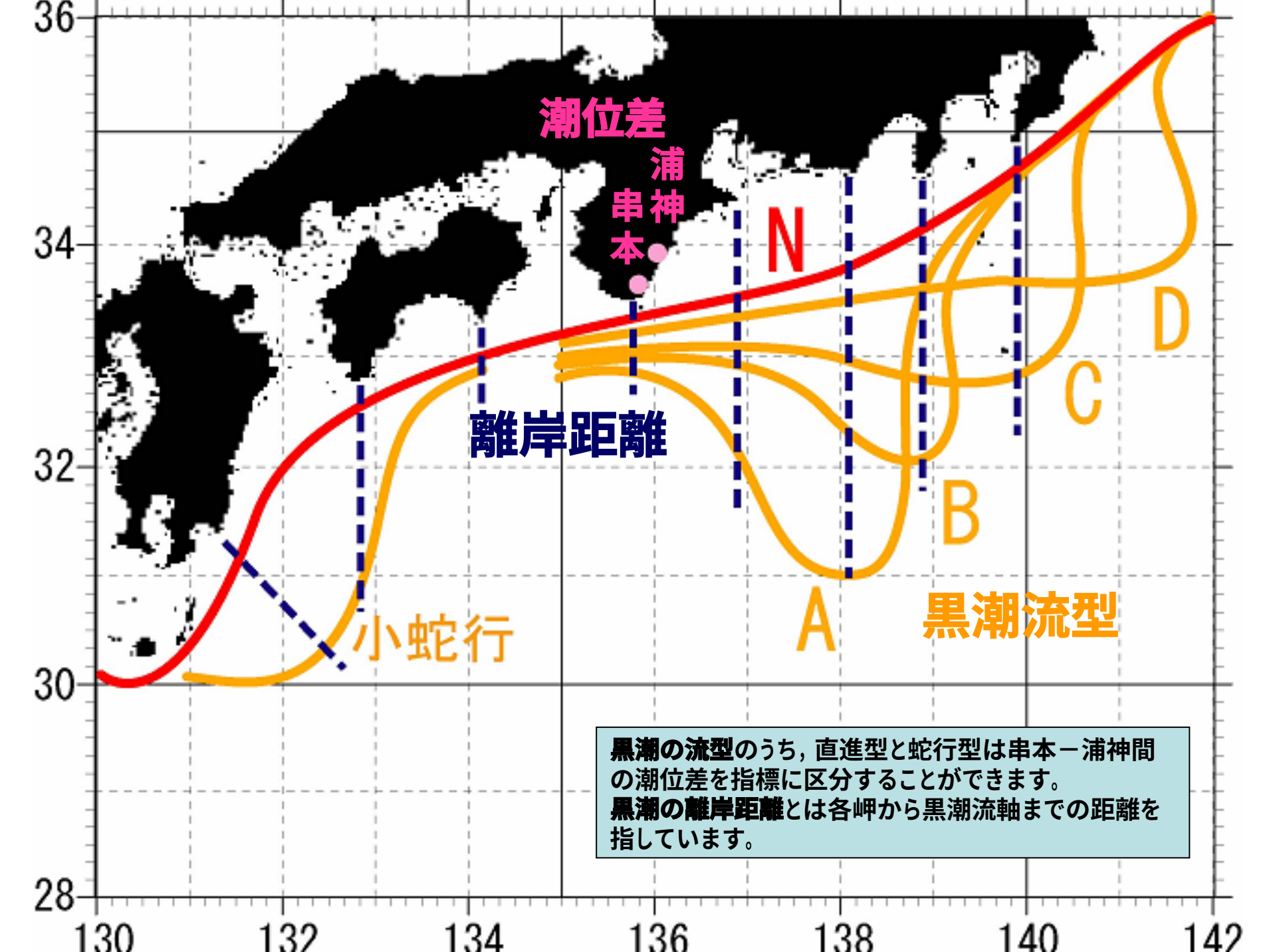

黒潮の流型のうち，直進型と蛇行型は串本－浦神間の潮位差を指標に区分することができます。
黒潮の離岸距離とは各岬から黒潮流軸までの距離を指しています。

黒潮が大蛇行していた期間

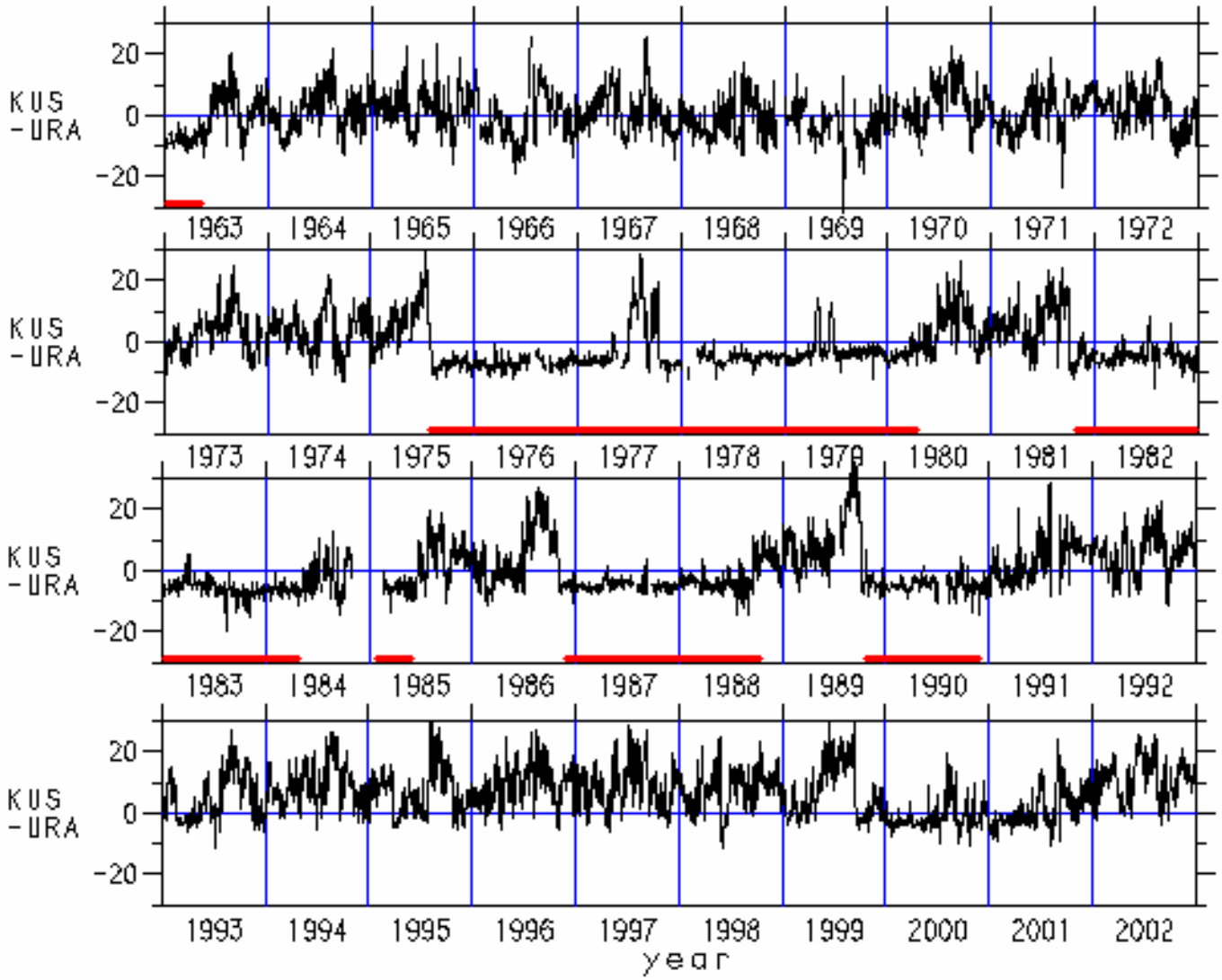

黒潮の大蛇行（A型）の様子は，紀伊半島南部に位置する2箇所の検潮所（串本と浦神）の潮位に差があるかどうかを調べればよいことがわかっています。図にはその潮位差が年毎にどのように変化したかを示しました。赤線は黒潮が大蛇行（A型）していたことを示しています。

「潮位データによる黒潮のモニタリング（黒潮の流路情報）」より抜粋
（東京大学海洋研究所提供，http：／／cer．ori．u－tokyo．ac．jp／tides／）

黒潮の流型変化の様子

西暦（年号）	1月		2月		3月		4月		5月		6月		7月		8月		9月		10月		11月		12月	
1965（昭40）	D	C	N	N	N	N	N	N	N	N	B	B	B	C	D	C	D	D	N	N	N	D	N	N
1966	N	N	C	C	C	C	C	C	C	B	B	B	D	D	B	N	D	N	N	N	N	N	B	B
1967	D	D	C	N	N	N	N	N	N	N	N	N	B	B	B	N	B	B	N	N	N	N	N	N
1968	N	C	C	C	C	C	C	C	C	C	N	N	N	N	N	N	N	N	N	N	N	N	N	N
1969	D	N	N	N	N	N	D	D	B	B	B	B	C	C	B	B	C	C	B	B	C	C	D	C
1970（昭45）	C	C	C	C	C	C	C	C	D	D	N	N	N	N	N	N	N	N	N	N	B	C	D	D
1971	C	C	C	C	C	C	C	C	C	C	D	D	N	N	N	N	B	B	D	C	N	N	N	N
1972	N	N	N	N	N	N	D	N	N	N	N	N	N	N	N	N	N	N	N	N	N	B	C	C
1973	N	B	N	N	N	N	C	N	N	N	N	N	N	N	N	N	N	N	N	N	N	N	N	N
1974	N	N	N	N	N	N	N	N	N	N	B	B	B	D	N	N	N	N	N	N	N	N	N	N
1975(昭50)	N	N	D	D	D	N	N	N	N	N	N	N	N	N	N	A	B	B	B	B	B	B	A	A
1976	A	A	A	A	A	A	A	A	A	A	A	A	A	A	A	A	A	A	A	A	A	A	A	A
1977	A	A	A	A	A	A	A	A	A	A	A	N	N	A	A	A	A	A	A	A	A	A	A	A
1978	A	A	A	A	A	A	A	A	A	A	A	A	A	A	A	A	A	A	A	A	A	A	A	A
1979	A	A	A	A	A	A	A	A	A	A	A	A	A	A	B	B	B	B	B	B	B	B	B	B
1980（昭55）	B	B	B	B	B	C	C	C	C	C	D	C	C	C	N	N	N	N	N	N	N	N	N	B
1981	B	B	B	B	B	N	N	N	N	N	B	D	D	N	N	N	N	D	D	B	B	C	B	C
1982	C	C	C	C	C	B	B	B	B	C	C	C	C	B	B	B	B	B	B	B	C	C	C	C
1983	C	B	B	C	C	C	C	B	B	B	B	B	B	C	C	C	C	B	C	C	C	B	B	B
1984	C	C	C	C	C	C	C	C	C	C	C	C	C	C	C	D	D	N	N	C	C	C	C	C
1985（昭60）	C	C	B	B	C	C	C	C	C	B	B	C	C	C	C	C	D	N	N	N	C	C	C	D
1986	N	N	N	N	CD	WC	C	C	C	C	N	N	N	C	C	N	N	N	C	N	N	N	A	A
1987	A	A	A	A	A	A	A	A	A	A	A	A	A	A	A	A	A	A	A	A	A	A	A	A
1988	C	B	B	B	C	B	B	C	B	C	C	C	C	C	C	C	C	N	N	C	C	C	C	CD
1989（平1）	B	C	C	C	C	DW	C	N	N	N	N	N	N	N	N	N	N	N	N	DN	B	A	A	A
1990（平2）	A	A	A	A	A	A	A	A	A	A	A	A	A	A	A	A	A	A	A	AC	C	C	C	CD
1991	C	C	C	C	C	C	C	C	C	CD	C	C	C	C	C	C	D	NN	N	N	N	N	N	N
1992	C	DC	N	N	N	N	N	BD	C	DN	N	N	N	N	D	N	N	N	N	NC	C	N	N	N
1993	N	N	N	N	N	B	B	BC	C	C	C	C	C	C	C	N	B	C	D	N	N	N	N	N
1994	B	C	D	N	N	N	C	C	NN	N	N	N	B	BN	N	N	N	N	N	N	N	N	N	N
1995（平7）	NN	N	N	N	N	N	B	B	B	C	C	C	D	D	NN	N	N	N	N	N	N	BC	C	CD
1996	C	D	D	D	W	D	N	N	N	N	N	N	N	N	N	N	N	N	N	N	B	C	D	N
1997	N	D	D	D	C	C	C	CW	D	ND	N	D	C	CNC	D	W	N	C	D	N	N	N	B	C
1998	D	C	N	N	D	N	NW	N	N	N	NB	B	B	C	C	C	C	N	N	BC	C	C	C	C
1999	CW	W	WB	C	C	C	C	C	N	N	N	N	N	N	N	N	N	BN	B	B	B	B	C	C
2000（平12）	C	C	CW	W	W	WB	B	BC	CW	WB	C	C	C	C	C	C	C	C	C	C	CW	CW	CB	B
2001	C	C	C	C	C	C	C	C	W	B	C	C	C	C	C	WB	BC	C	C	CD	DW	WD	DN	C
2002	N	N	N	N	N	N	N	N	NB	N	N	N	N	N	N	N	N	N	N	N	N	N	N	N
2003	N	N	N	N	N	N	B	NW	WN	B	BC	D	N	ND	N	N								

・本州南岸における黒潮の流型（A，B，C，D，N型）を旬毎に分類し，A型を赤色，B型をピンク色，C型を黄色，D型を緑色，N型を水色，その他を白色に色分けして示しました。
・A型とN型は継続性があること，B，C，D型は短期的に変化していることなどがわかります。

海洋速報（海上保安庁海洋情報課）および一都三県漁海況速報を基に，静岡県水産試験場が作成した表を一部改訂した。

日本南岸海域における黒潮の離岸距離の時間変動

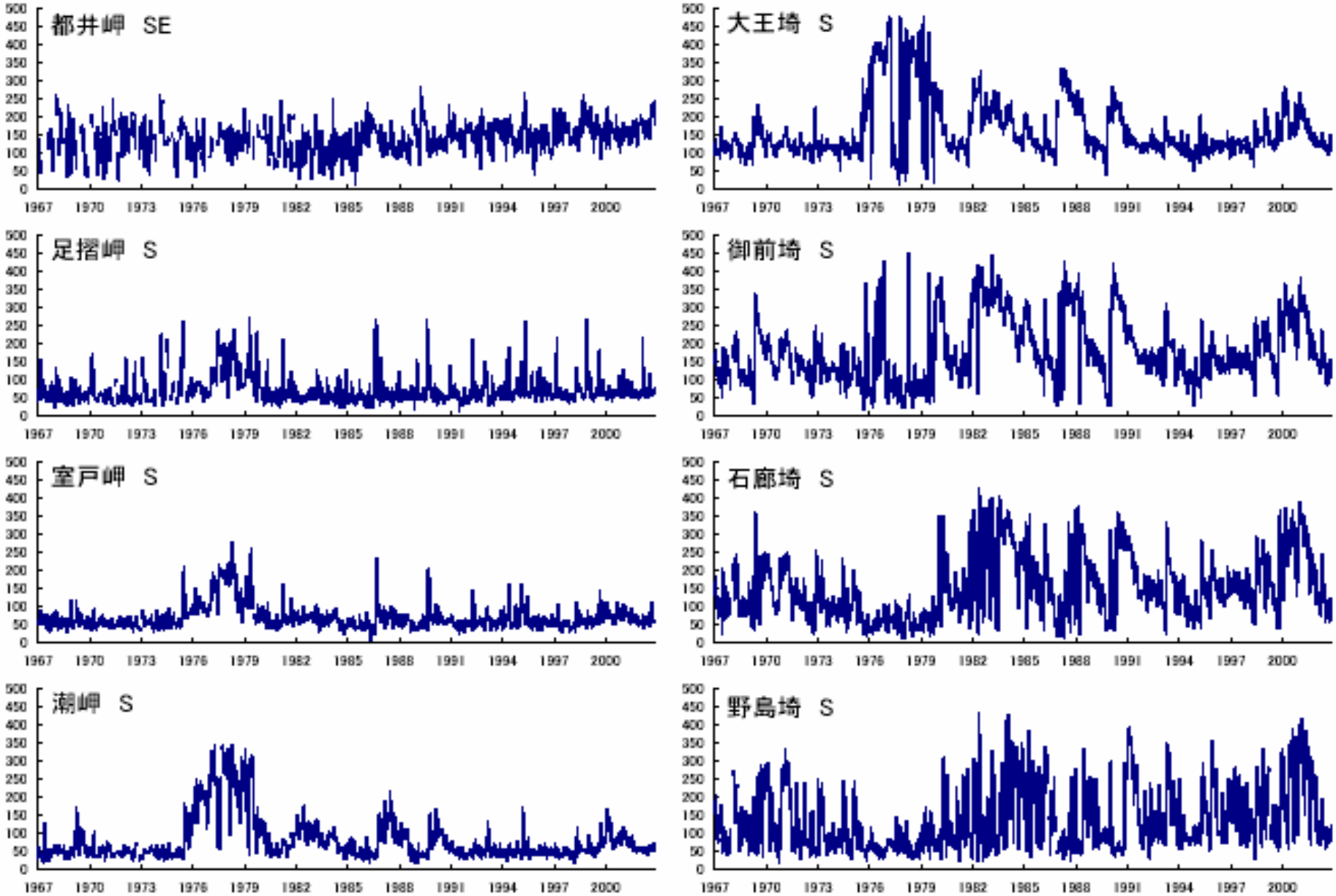

各岬から特定の方向へ向けて測った黒潮流軸までの距離の時間変化で，
例えば都井岬SEならば，都井岬から南東に何km離れたところに黒潮流軸があるかを示しています。