日本海の海況を特徴づける海洋構造

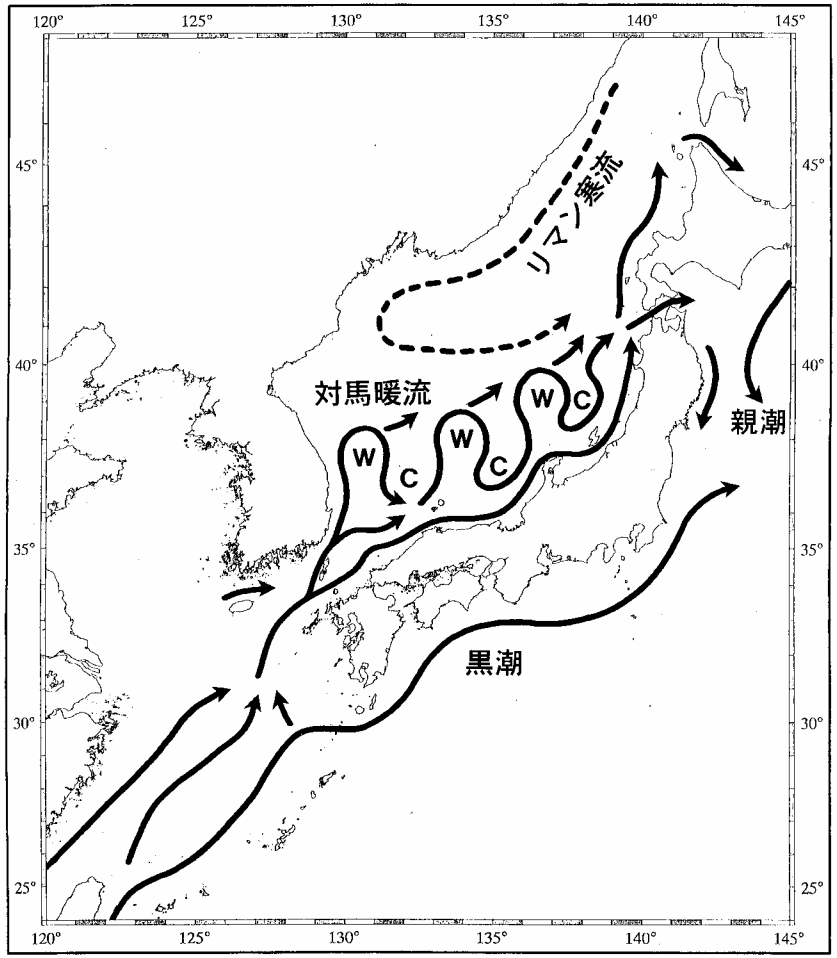

1) 対馬暖流：対馬東水道に由来する沿岸分枝（第1分枝）の流路は安定しているのに対し，対馬西水道由来の沖合分枝（第2分枝）及び東朝鮮海流（第3分枝）の流路の変動は大きい．沖合分枝及び東朝鮮暖流の流路については，100m深水温分布のフロント域を追跡することで把握可能である．

2) 冷 水 域：100m深水温分布に基づいて，周辺海域よりも水温が低い海域を「冷水域」と見なしている．島根沖，山陰・若狭沖，佐渡沖，入道埼沖でみられる場合が多い．

3) 暖 水 域：200m深水温分布に基づいて，周辺海域よりも水温が高く，等温線が閉じている海域を「暖水域」と見なしている．隠岐諸島東方で発生し，東～北東へ移動するパターンが一般的．ただし，同一海域に数ヶ月以上留まることも多い．

対馬暖流とは

対馬暖流は，奄美大島北西海域で黒潮から派生した流れのほか，台湾北東海域で陸棚上を北上する流れ（黒潮分派）や台湾海峡を通過する流れ（台湾暖流）が東シナ海中部で合流し，形成される．対馬海峡を通過した対馬暖流は3つの分枝流（沿岸分枝・沖合分枝・東朝鮮暖流）に分かれることが多いが，北上とともに合流・分岐を経ながら津軽海峡・宗谷海峡を経て太平洋・オホーツク海へ流出する．対馬暖流が時計回りに流れる海域で暖水域（W）が，反時計回りに流れる海域で冷水域（C）が出現する場合が多い．

海況日本海指標①50m深平均水温偏差

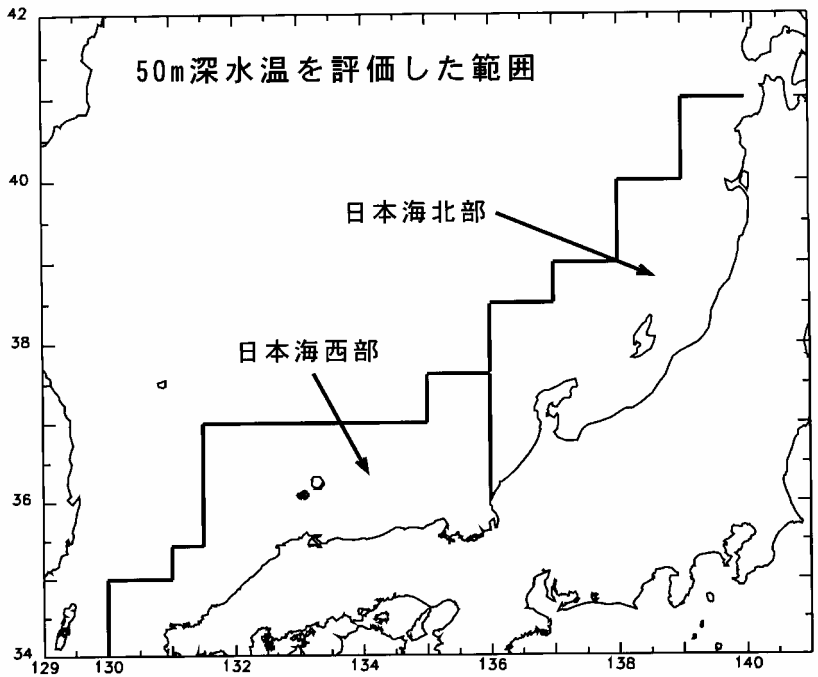

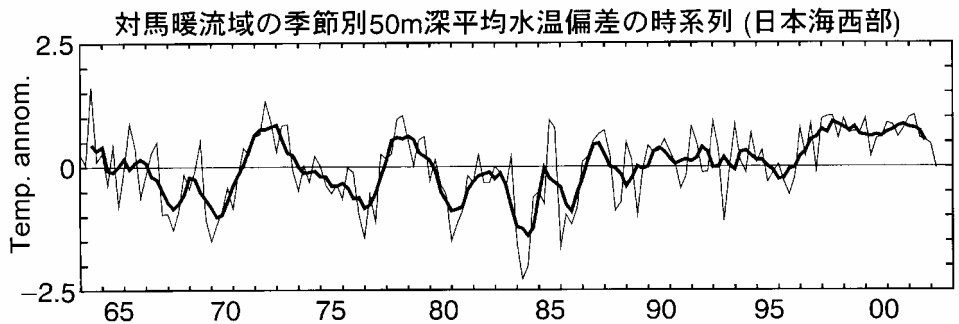

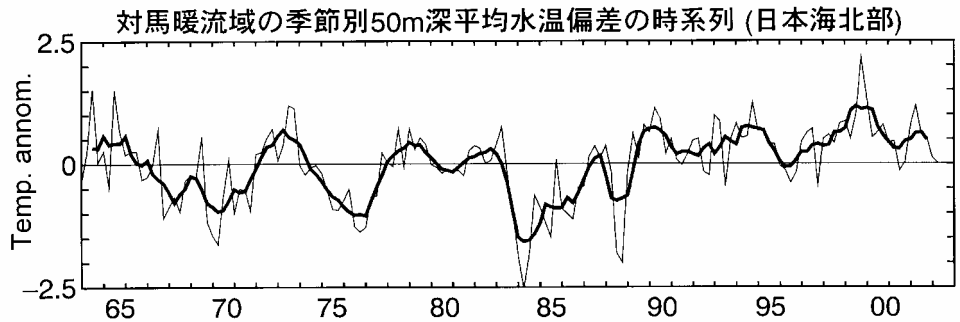

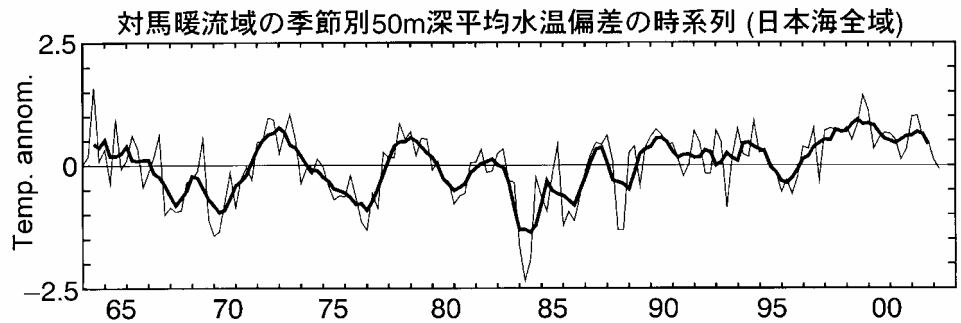

対馬暖流域における50m深の平均水温偏差(その季節の平年値からのずれ) の時系列. 太線は5季節の移動平均水温を示す

海況日本海指標②主要4冷水域の面積占有率

各冷水域の占有率を求めた規定水域

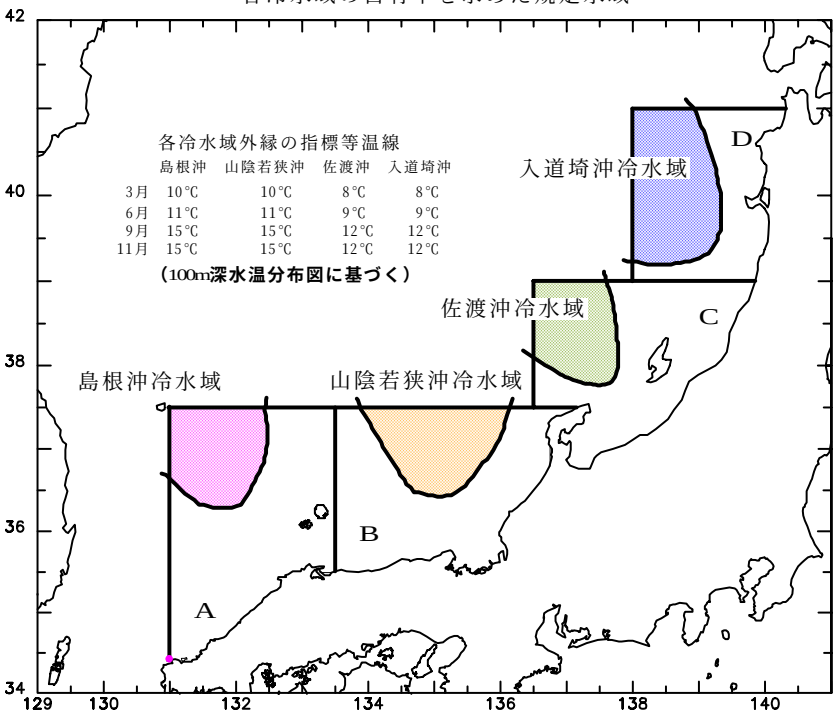

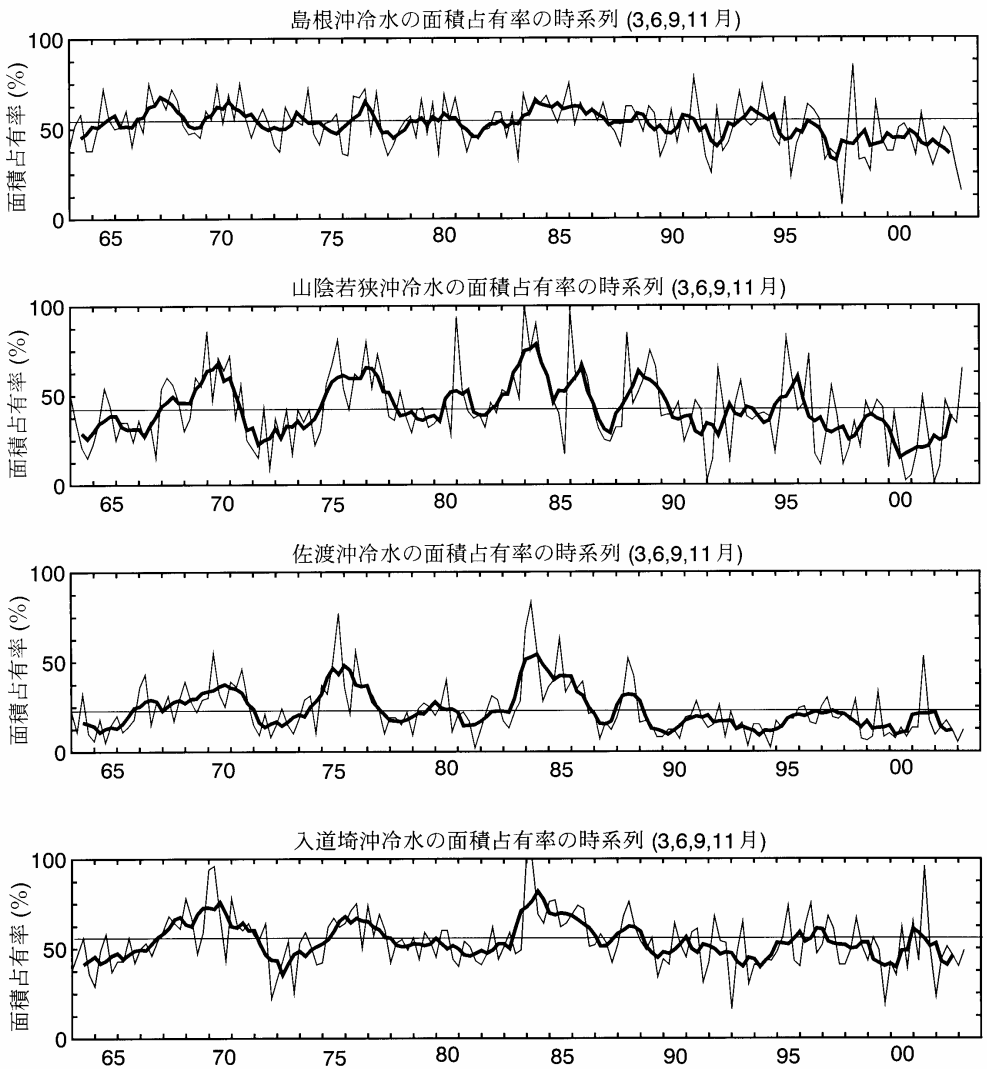

3, 6, 9, 11月の100m深水温分布図に基づく，日本海の代表的な4つの冷水域の各冷水域の面積占有率。太線は5個の移動平均を示す。

面積占有率.
　太線と海岸線に囲まれた規定水域 (A〜D)の中で，各冷水域が占める面積の割合(%)。

海況日本海指標③暖水域の移動

現在のところ，暖水域の分布･移動を的確に評価できる指標を持ち合わせていない．このため，毎月の200m深水温分布から暖水域と見なすことができるものを抜き出して（右図），それらの分布を追跡することにより，暖水域の移動を調べている．

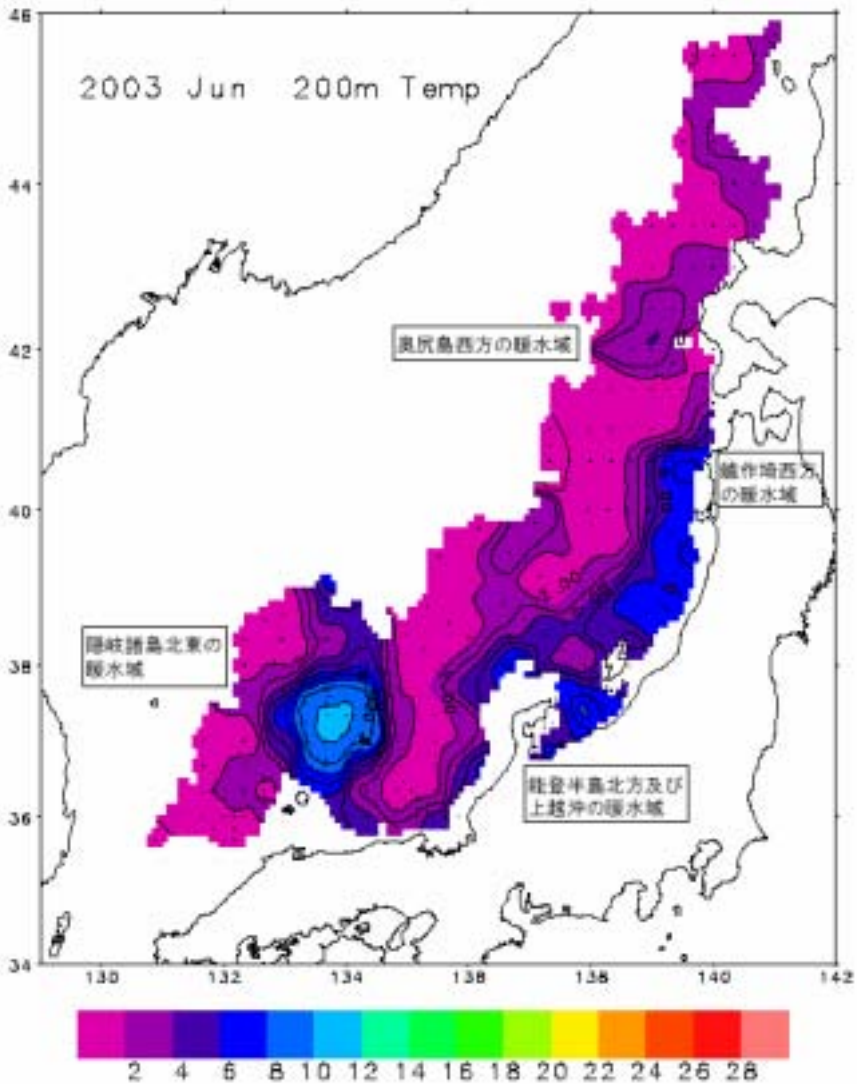
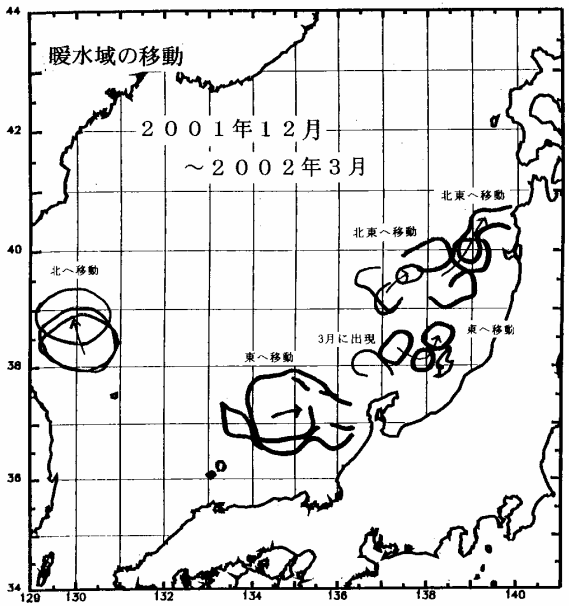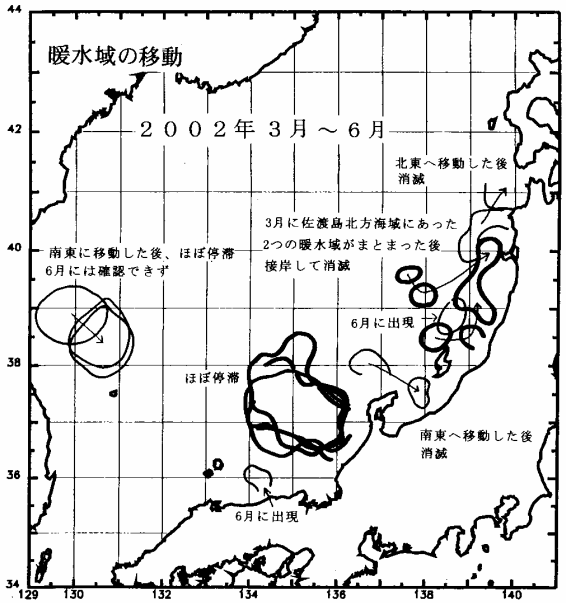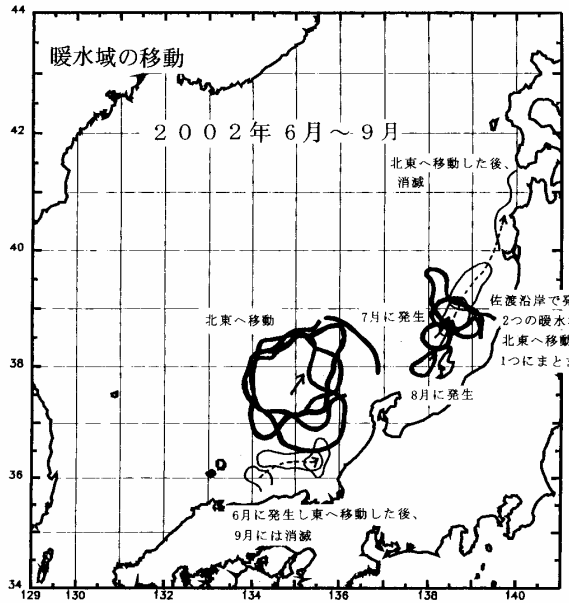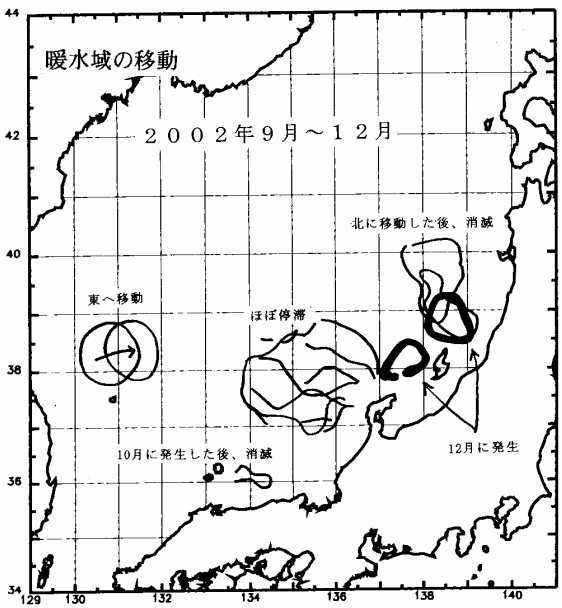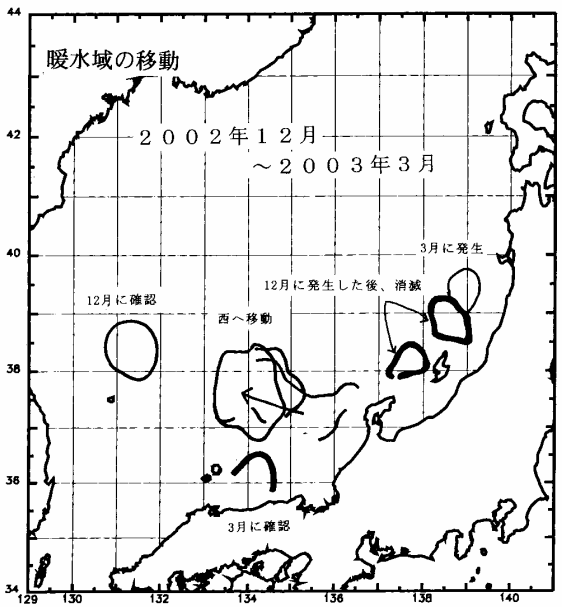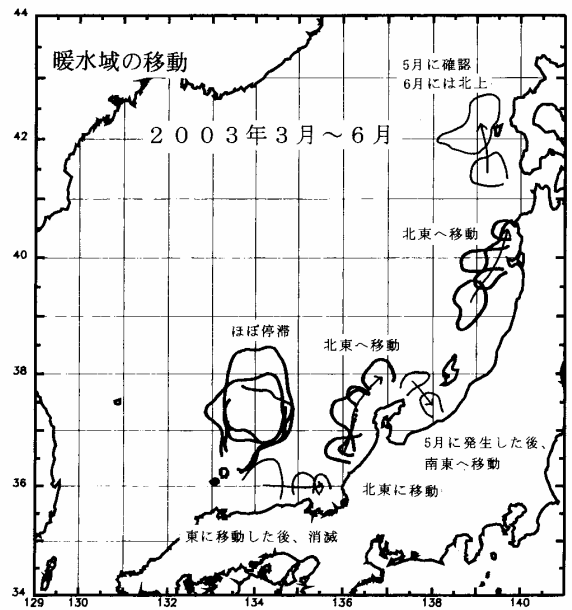
2001年12月～2003年6月の暖水域の移動