北海道周辺の海洋構造

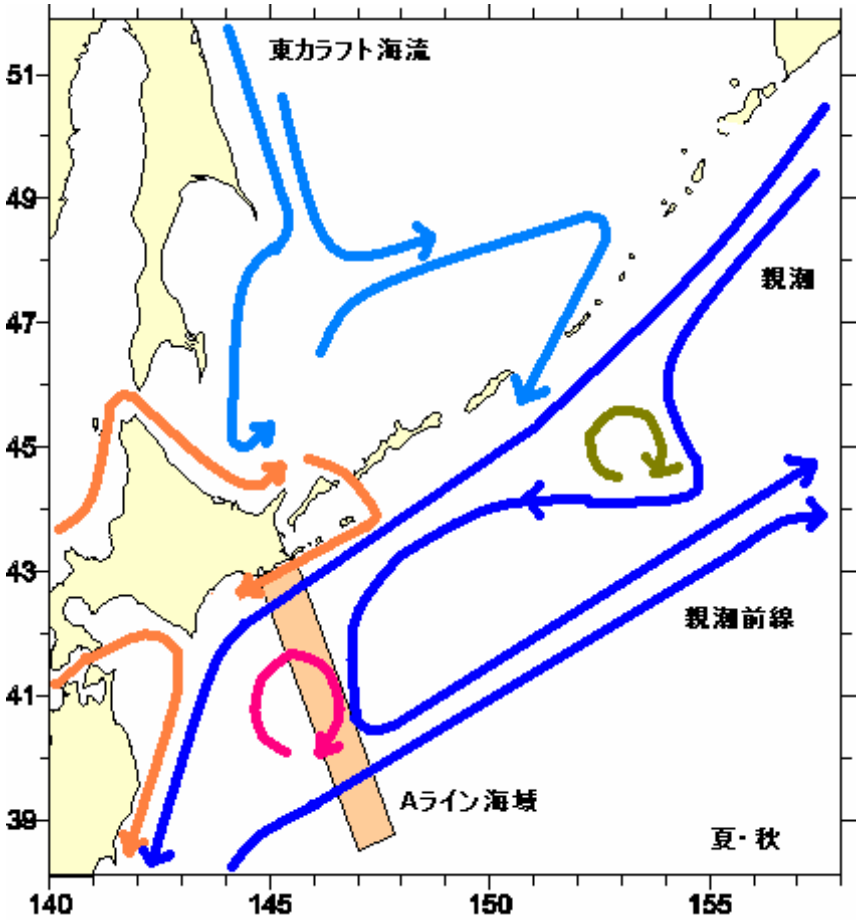

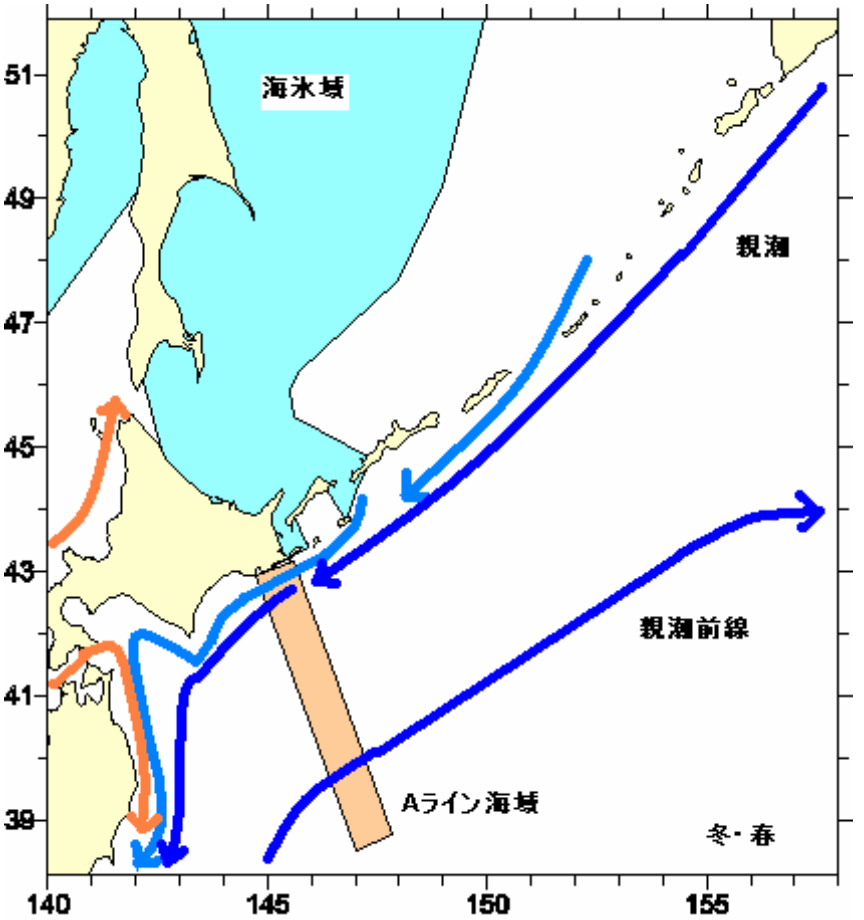

この海域では親潮が強かったか弱かったのか、岸よりであったのかそうでなかったのか、またオホーツクの海氷の状況がどのようなものであったかが、この海域の生産性に影響します。そこで、親潮の構造のモニタリングのために、厚岸沖のAラインを、またオホーツクの海氷の状況をモニタリングしています。

厚岸沖A-lineにおける水温塩分の変化



Aライン海域の表面水温（上）と表面水の塩分（下）の時系列(1987～2003年)

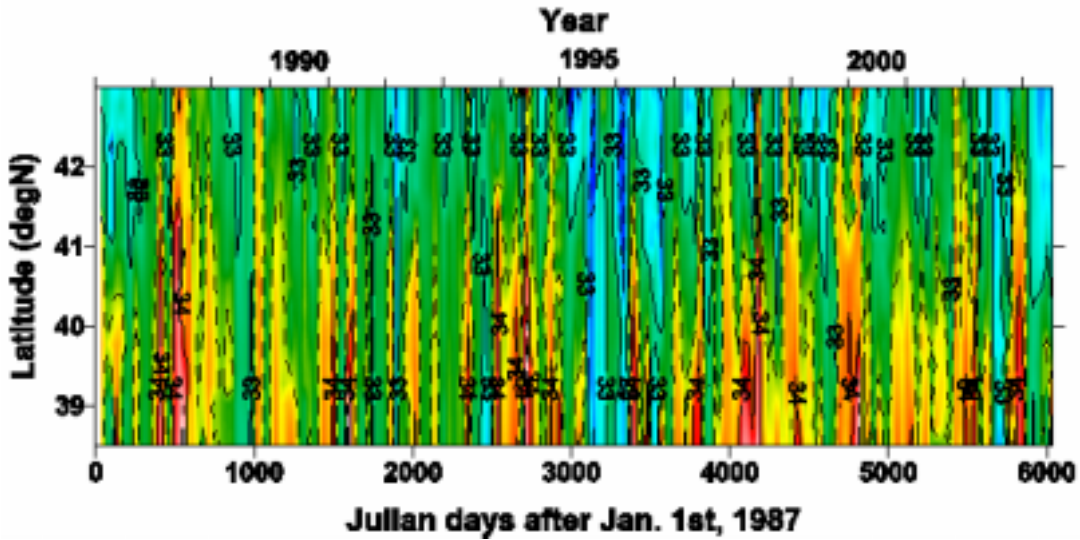

A-lineを観測を始めた1987年からの表面の水温･塩分の時間変化。横軸が年、縦軸は定線の緯度で上は北海道のすぐ近く、下は沖合いを表している。色合いは水温では青いほど温度が低く、赤くなるにつれて温度が高くなることを意味している。また、塩分では青いほど塩分が低く、赤くなるにつれて塩分が高いことを示している。

年により温度･塩分が大きく異なっていることがわかる。

オホーツク氷の様子

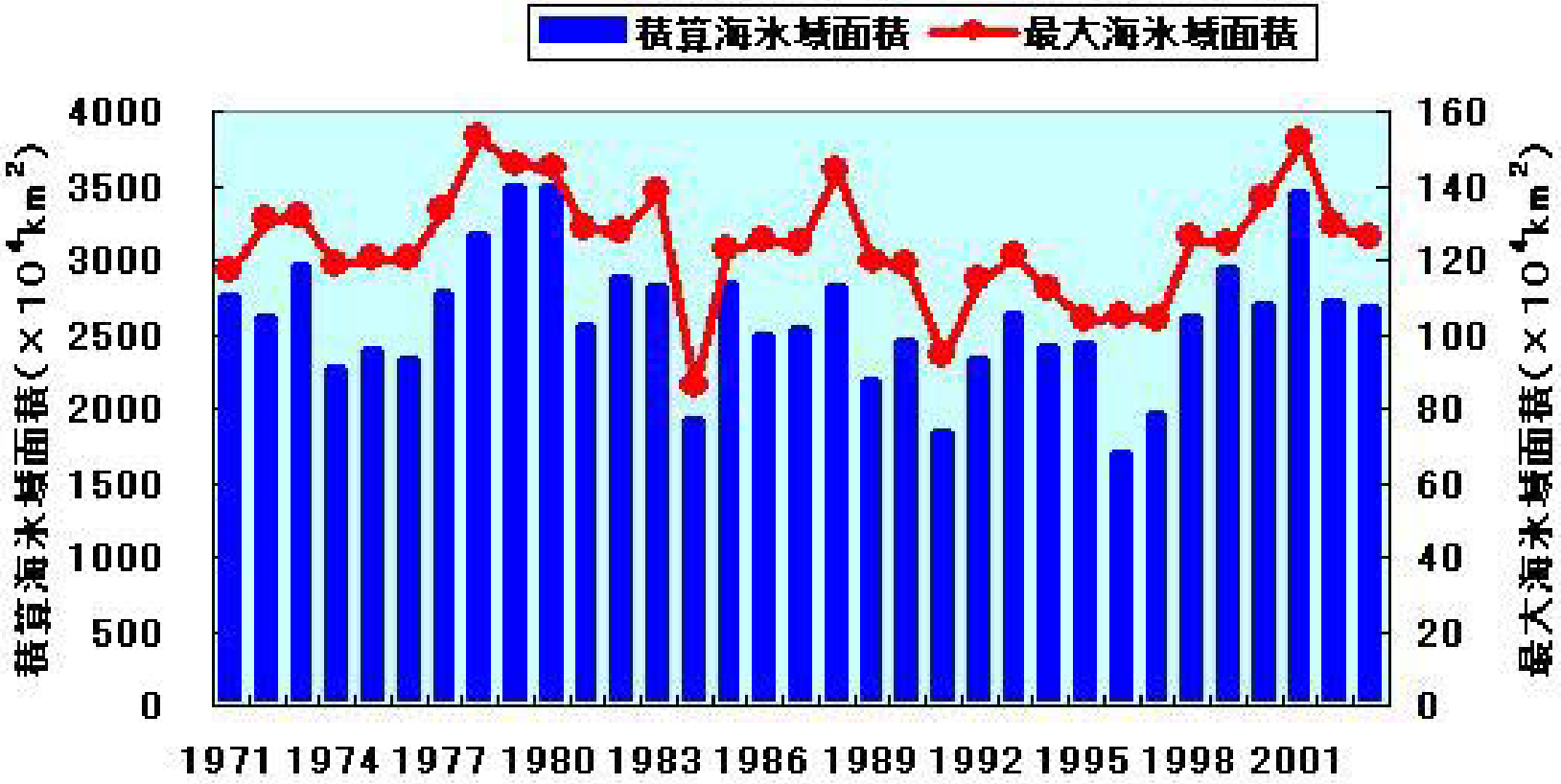

？海上保安庁が週1回出しているオホーツクの海氷の被覆度から出したその冬の最大海氷面積と海氷面積の積算値です。この量はオホーツクにおける春の生産量に関連していると考えられています